Étude sur l’eau potable

Tony WENG

DWFA

Contexte

L’ONG DWFA (Drinking Water For All) présente 3 domaines d’expertise :

1. Création de services d’accès à l’eau potable
2. Modernisation de services d’accès à l’eau déjà existants
3. Consulting auprès d’administrations/gouvernements à propos des politiques d’accès à l’eau

Contexte

Dans le but d’investir dans un de ces domaines d’expertise dans un pays encore indéterminé, nous avons besoin d’un tableau de bord pour :

- Identifier les pays qui rencontrent des difficultés d’accès à l’eau potable;
- Identifier ceux pour lesquels concentrer nos efforts.

Données

- 4 bases de données :
  - Données sur la population
  - Données sur l'accès à l'eau potable
  - Données sur le taux de mortalité en 2016
  - Données sur la stabilité politique
- 1 base de données géographiques

Prétraitement des données

- Vérification des types de données
- Suppression de lignes/colonnes
- Création d’un ID
- Jointure des tables
- Agrégation de la population
- Création d’une table « Total »

Visualisation

- 3 vues :
  - Vue « Mondiale »
  - Vue « Continentale »
  - Vue « Nationale »

- Différents filtres utilisables par l'utilisateur.

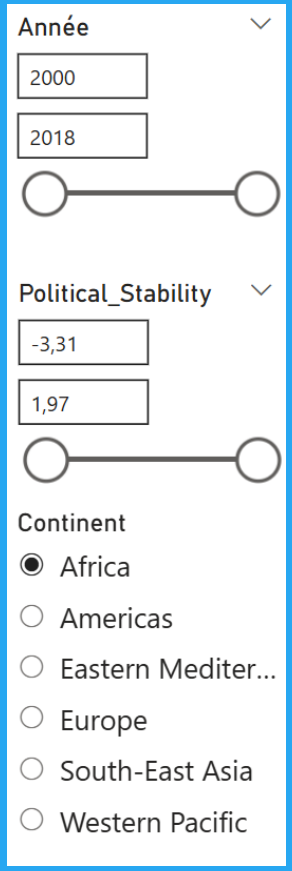

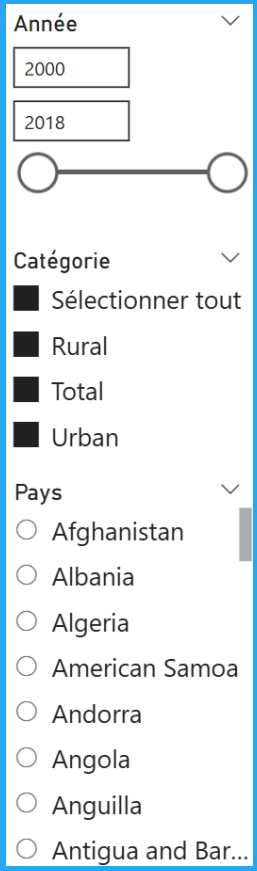

Vue Mondiale

- Taux de mortalité en 2016
- L’évolution de l’accès à l’eau potable dans le monde
- L’évolution de la population
- L’évolution de la répartition de la population
- Carte mondiale d’accès à l’eau potable

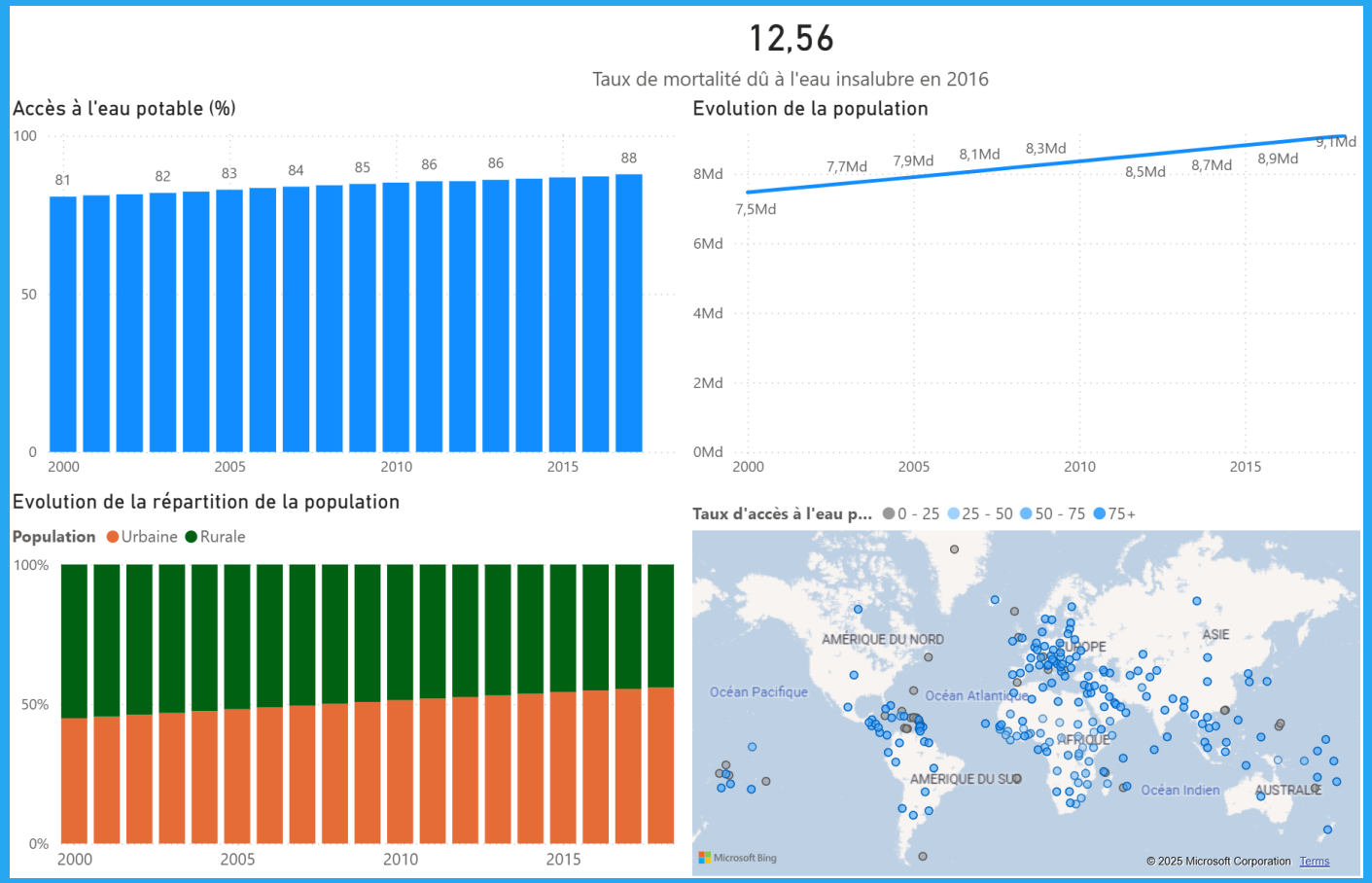

Vue Continentale

- Taux de mortalité en 2016
- Taux d’accès à l’eau potable et le taux de population urbaine par pays
- Stabilité politique et efficacité politique en 2016 par pays
- L’évolution et la répartition de la population
- Qualité des infrastructures par pays

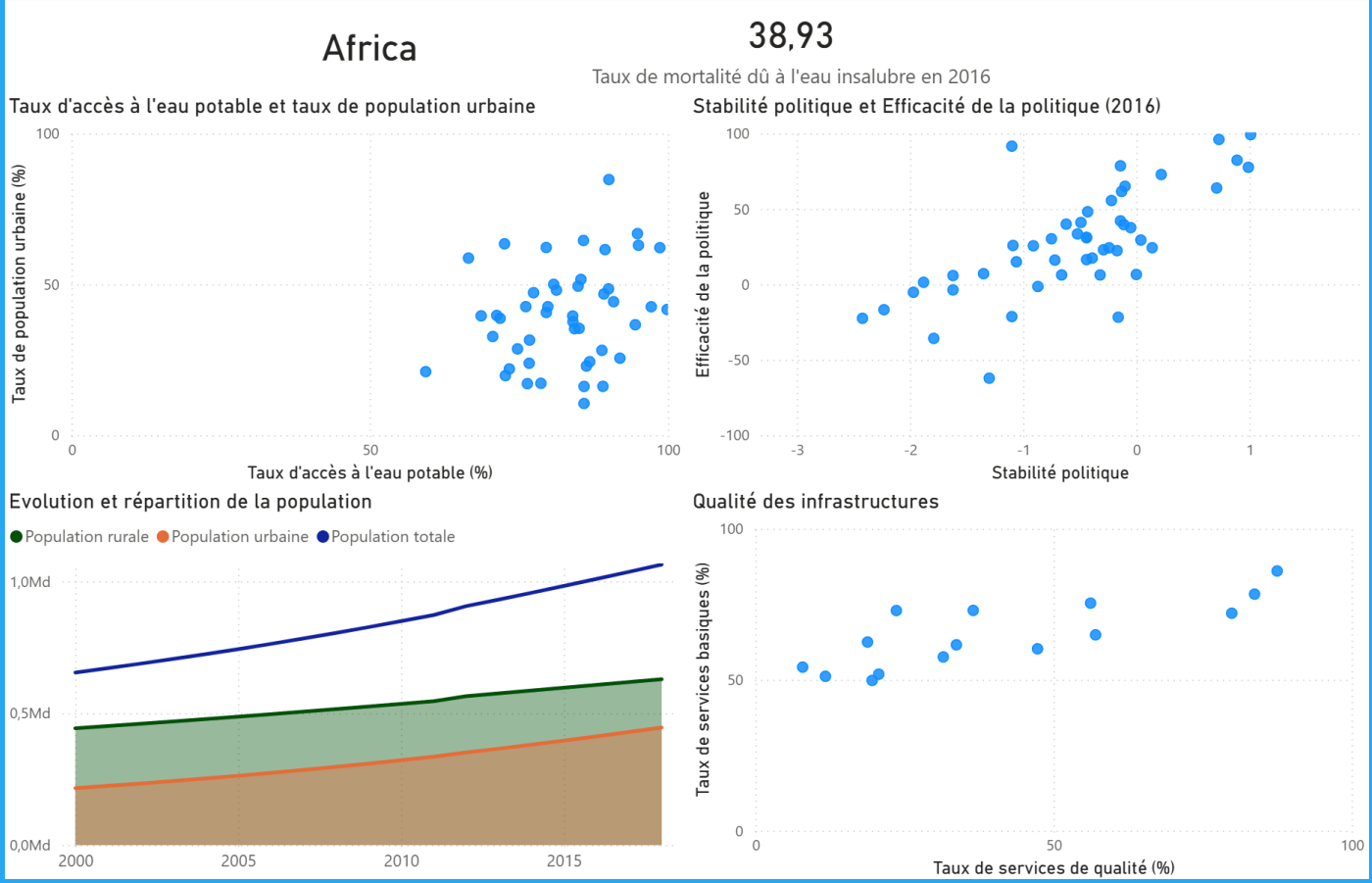

Vue Nationale

- Taux de mortalité en 2016
- L'évolution du taux d'accès à l'eau potable et le taux de population urbaine
- L'évolution de la stabilité politique
- L'évolution et la répartition de la population
- L'évolution de la qualité des infrastructures

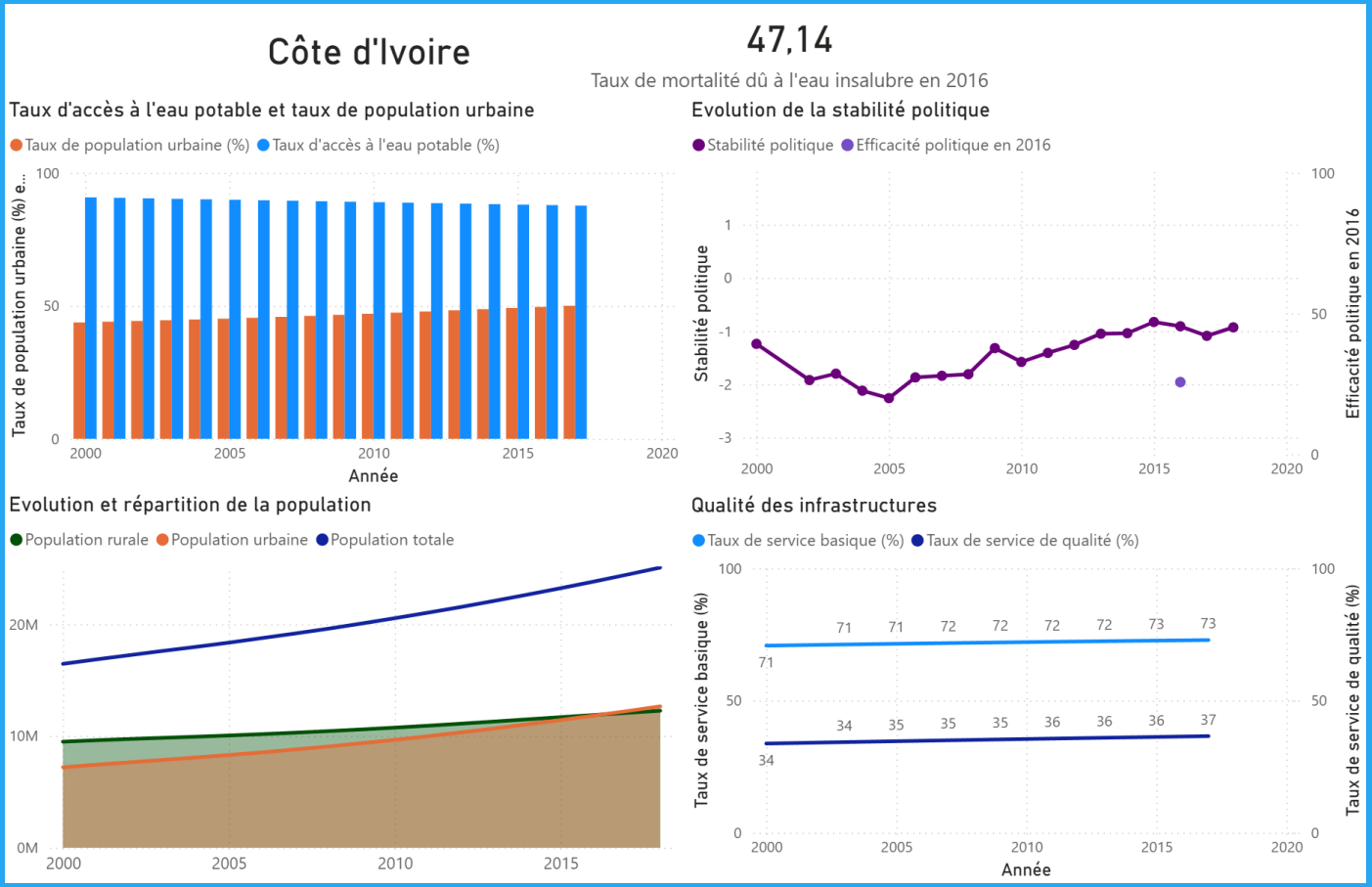

Création de services

- Sur la vue mondiale, la carte du taux d’accès à l’eau potable.
- Sur les vues continentale et nationale, les graphiques combinant le taux d’accès à l’eau potable et le taux de population urbaine.

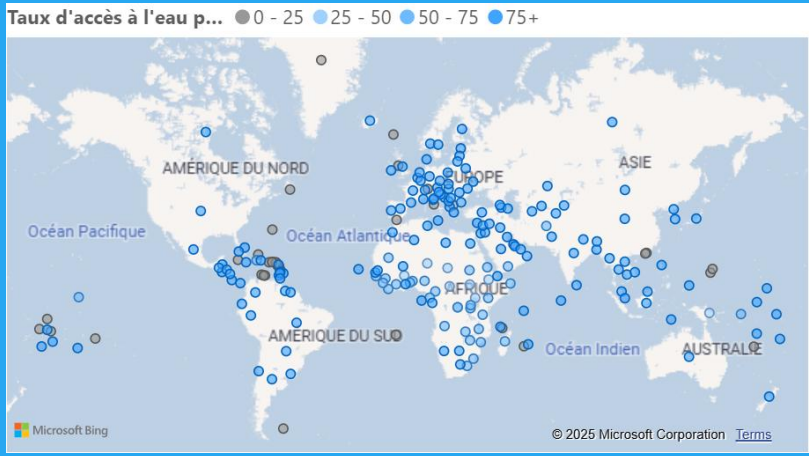

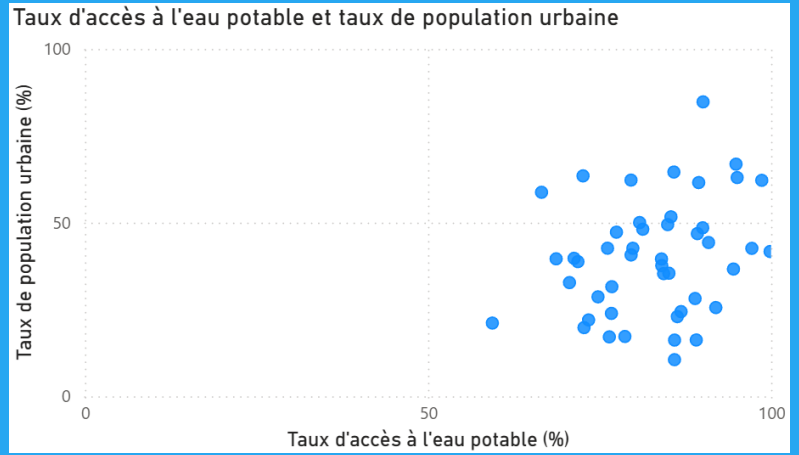

Modernisation des services

- Sur les vues continentale et nationale, les graphiques décrivant la qualité des infrastructures.

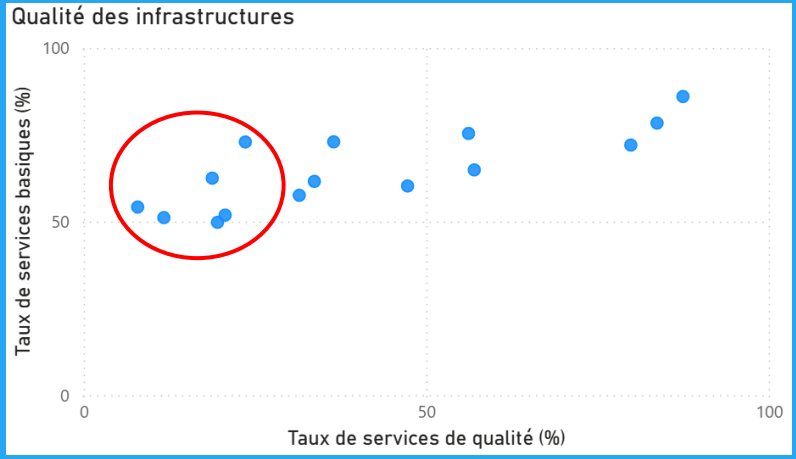

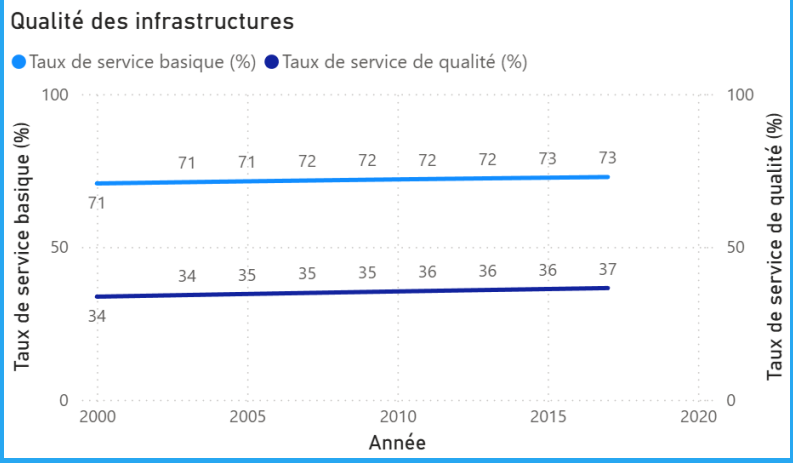

Consulting
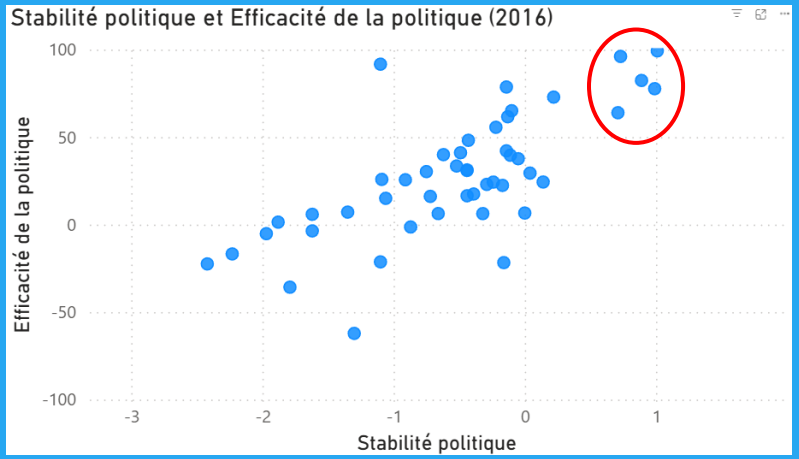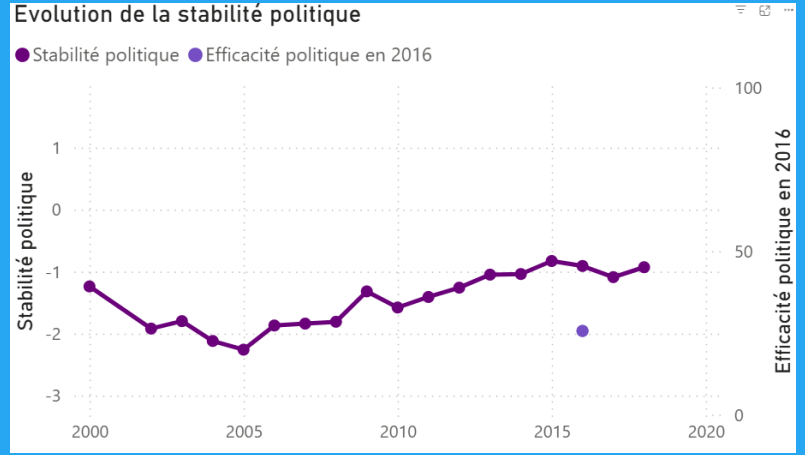
- Sur les vues continentale et nationale, les graphiques combinant l'efficacité politique gouvernementale d'accès à l'eau et la stabilité politique.